CERTIFICADO DE PROPIEDAD

QUE EL INSTITUTO DE VIVIENDA DE QUINTANA ROO, A TRAVES DEL C. ING. MARIO ERNESTO VILLANUEVA MADRID Y C. LIC. VICTOR MANUEL VIVAS GONZALEZ, EN SUS CARACTERES DE PRESIDENTE Y CONSEJERO VOCAL MUNICIPAL DEL CONSEJO DIRECTIVO DEL INVIQROO Y EN USO DE LAS FACULTADES QUE LES CONFIERE LOS ARTICULOS SEPTIMO Y 13 FRACCION V DE LA LEY DE CREACION DEL PROPIO INSTITUTO, HAN TENIDO A BIEN EXPEDIR EN FAVOR DE:

SOCORRO NIDELVIA TRINCHAN MENDOZA

RESPECTO A UNA SUPERFICIE DE TERRENO DE 220.00 METROS CUADRADOS, MARCADO COMO LOTE 11, MANZANA 103 DE LA RESERVA TERRITORIAL DEL INVIQROO

UBICADA EN LA CIUDAD DE COZUMEL MUNICIPIO DE COZUMEL QUINTANA ROO, CON LAS SIGUIENTES MEDIDAS Y COLINDANCIAS:

AL NORTE: 22.00 MTS. CON LOTE 12
AL SUR : 22.00 MTS. CON LOTE 10
AL ESTE : 10.00 MTS. CON LOTE 08
AL OESTE: 10.00 MTS. CON CALLE

CALLE CATASTRAL: 4012210311

EL PRESENTE CERTIFICADO DE PROPIEDAD, SE EXTIENDE DE CONFORMIDAD A LAS NORMAS ESTABLECIDAS EN EL CODIGO CIVIL VIGENTE Y LA LEY DEL INSTITUTO DE VIVIENDA, AMBAS DEL ESTADO DE QUINTANA ROO Y EN BASE AL EXPEDIENTE RELATIVO AL CONTRATO CELEBRADO EL DIA 30 DE JULIO DE 1991 4 DE OCTUBRE DE 1994 POR EL CUAL EL INVIQROO VENDIO EL LOTE DE TERRENO A SOCORRO NIDELVIA TRINCHAN MENDOZA CON EL FIN DE PROCURAR Y CONSOLIDAR EL PATRIMONIO INMOBILIARIO DE LA FAMILIA QUINTANARROENSE.

DADO EN LA CIUDAD DE CHETUMAL MUNICIPIO DE OTHON P. BLANCO ESTADO DE QUINTANA ROO, A LOS OCHO DIAS DEL MES DE JUNIO DE MIL NOVECIENTOS NOVENTA Y OCHO

PRESIDENTE DEL CONSEJO

ING. MARIO VILLANUEVA MADRID

CONSEJERO MUNICIPAL

LIC. VICTOR MANUEL VIVAS GONZALEZ

ESTADOS UNIDOS MEXICANOS

Despacho ... Ciudad Che... Quintana Roo, Méx.

No. DE FOLIO 2203

PARA LOS EFECTOS LEGALES QUE PROCEDAN, EL INVIQROO MANIFIESTA:

1.-QUE LA FRACCION DE TERRENO OBJETO DE ESTE CERTIFICADO DE PROPIEDAD, SE ENCUENTRA DENTRO DE UNA SUPERFICIE MAYOR DE SU PATRIMONIO, TAL Y COMO CONSTA, POR LA EXHIBICION DE LA ESCRITURA PUBLICA NUMERO 2255 DE FECHA 10 DE SEPTIEMBRE DE 1986 MISMA QUE SE HAYA INSCRITA EN EL REGISTRO PUBLICO DE LA PROPIEDAD Y DEL COMERCIO DE LA CIUDAD DE CHETUMAL, QUINTANA ROO, EL DIA 25 DE AGOSTO DE 1987, BAJO EL NUMERO 45 A FOJAS 170 A 173 DEL TOMO I SECCION QUINTA.

2.- QUE LA SUBDIVISION DE LA SUPERFICIE MAYOR ENUNCIADA EN LA DECLARACION QUE ANTECEDE, QUEDO INSCRITA A FOJAS 17 A 36 DEL TOMO CCLXXIX SECCION PRIMERA DEL REGISTRO PUBLICO DE LA PROPIEDAD Y DEL COMERCIO DE LA CIUDAD DE CHETUMAL QUINTANA ROO Y DE LA QUE RESULTA EL LOTE DE TERRENO QUE SE DESINCORPORA DE SU PATRIMONIO.

3.- QUE SE CONVINO COMO PRECIO DE LA OPERACION CITADA EN EL CONTRATO DE COMPRAVENTA CON RESERVA DE DOMINIO Y CONVENIO MODIFICATORIO LA CANTIDAD DE $ 3,425.4

CANTIDAD QUE EL INVIQROO HA RECIBIDO EN BUENAS MONEDAS DE CURSO LEGAL. Traspasado Virtualmente 17/11/04

CROQUIS DE LOCALIZACION

REG. PUBLICO DEL COM.
TRASPASO
NÚM. FOLIO
FECHA
CHETUMAL, Q. ROO

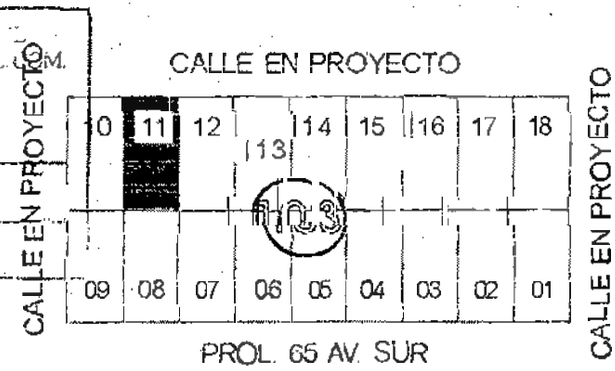

EL CONTENIDO DE ESTE DOCUMENTO REGISTRADO HOY A LAS 14:12 HORAS, BAJO EL NUMERO 171 COMO PARTIDA ____ A FOJAS 605a 606 DEL TOMO CCCVIII, DEL REGISTRO PUBLICO DE LA PROPIEDAD Y DEL COMERCIO DE LA CIUDAD DE Chetumal QUINTANA ROO, A 15 DE Octubre DE 1998 Sección I.

Dirección del Registro Público de la Propiedad y del Comercio
Poder Ejecutivo
Estado de Q. Roo.

DIRECTOR DEL REGISTRO PUBLICO DE LA PROPIEDAD Y DEL COMERCIO

CERTIFICADO DE PROPIEDAD

QUE EL INSTITUTO DE VIVIENDA DE QUINTANA ROO, A TRAVES DEL C. ING. MARIO ERNESTO VILLANUEVA MADRID Y C. LIC. VICTOR MANUEL VIVAS GONZALEZ, EN SUS CARACTERES DE PRESIDENTE Y CONSEJERO VOCAL MUNICIPAL DEL CONSEJO DIRECTIVO DEL INVIQROO Y EN USO DE LAS FACULTADES QUE LES CONFIERE LOS ARTICULOS SEPTIMO Y 13 FRACCION V DE LA LEY DE CREACION DEL PROPIO INSTITUTO, HAN TENIDO A BIEN EXPEDIR EN FAVOR DE:

SOCORRO NIDELVIA TRINCHAN MENDOZA

RESPECTO A UNA SUPERFICIE DE TERRENO DE 220.00 METROS CUADRADOS, MARCADO COMO LOTE 11, MANZANA 103 DE LA RESERVA TERRITORIAL DEL INVIQROO

UBICADA EN LA CIUDAD DE COZUMEL MUNICIPIO DE COZUMEL QUINTANA ROO, CON LAS SIGUIENTES MEDIDAS Y COLINDANCIAS:

AL NORTE: 22.00 MTS. CON LOTE 12
AL SUR : 22.00 MTS. CON LOTE 10
AL ESTE : 10.00 MTS. CON LOTE 08
AL OESTE: 10.00 MTS. CON CALLE

CALLE CATASTRAL: 4012210311

EL PRESENTE CERTIFICADO DE PROPIEDAD, SE EXTIENDE DE CONFORMIDAD A LAS NORMAS ESTABLECIDAS EN EL CODIGO CIVIL VIGENTE Y LA LEY DEL INSTITUTO DE VIVIENDA, AMBAS DEL ESTADO DE QUINTANA ROO Y EN BASE AL EXPEDIENTE RELATIVO AL CONTRATO CELEBRADO EL DIA 30 DE JULIO DE 1991 4 DE OCTUBRE DE 1994 POR EL CUAL EL INVIQROO VENDIO EL LOTE DE TERRENO A SOCORRO NIDELVIA TRINCHAN MENDOZA CON EL FIN DE PROCURAR Y CONSOLIDAR EL PATRIMONIO INMOBILIARIO DE LA FAMILIA QUINTANARROENSE.

DADO EN LA CIUDAD DE CHETUMAL MUNICIPIO DE OTHON P. BLANCO ESTADO DE QUINTANA ROO, A LOS OCHO DIAS DEL MES DE JUNIO DE MIL NOVECIENTOS NOVENTA Y OCHO

PRESIDENTE DEL CONSEJO

ING. MARIO VILLANUEVA MADRID

CONSEJERO MUNICIPAL

LIC. VICTOR MANUEL VIVAS GONZALEZ

ESTADOS UNIDOS MEXICANOS

Despacho ... Ciudad Che... Quintana Roo, Méx.

No. DE FOLIO 2203

PARA LOS EFECTOS LEGALES QUE PROCEDAN, EL INVIQROO MANIFIESTA:

1.-QUE LA FRACCION DE TERRENO OBJETO DE ESTE CERTIFICADO DE PROPIEDAD, SE ENCUENTRA DENTRO DE UNA SUPERFICIE MAYOR DE SU PATRIMONIO, TAL Y COMO CONSTA, POR LA EXHIBICION DE LA ESCRITURA PUBLICA NUMERO 2255 DE FECHA 10 DE SEPTIEMBRE DE 1986 MISMA QUE SE HAYA INSCRITA EN EL REGISTRO PUBLICO DE LA PROPIEDAD Y DEL COMERCIO DE LA CIUDAD DE CHETUMAL, QUINTANA ROO, EL DIA 25 DE AGOSTO DE 1987, BAJO EL NUMERO 45 A FOJAS 170 A 173 DEL TOMO I SECCION QUINTA.

2.- QUE LA SUBDIVISION DE LA SUPERFICIE MAYOR ENUNCIADA EN LA DECLARACION QUE ANTECEDE, QUEDO INSCRITA A FOJAS 17 A 36 DEL TOMO CCLXXIX SECCION PRIMERA DEL REGISTRO PUBLICO DE LA PROPIEDAD Y DEL COMERCIO DE LA CIUDAD DE CHETUMAL QUINTANA ROO Y DE LA QUE RESULTA EL LOTE DE TERRENO QUE SE DESINCORPORA DE SU PATRIMONIO.

3.- QUE SE CONVINO COMO PRECIO DE LA OPERACION CITADA EN EL CONTRATO DE COMPRAVENTA CON RESERVA DE DOMINIO Y CONVENIO MODIFICATORIO LA CANTIDAD DE $ 3,425.4

CANTIDAD QUE EL INVIQROO HA RECIBIDO EN BUENAS MONEDAS DE CURSO LEGAL. Traspasado Virtualmente 17/11/04

CROQUIS DE LOCALIZACION

REG. PUBLICO DEL COM.
TRASPASO
NÚM. FOLIO
FECHA
CHETUMAL, Q. ROO

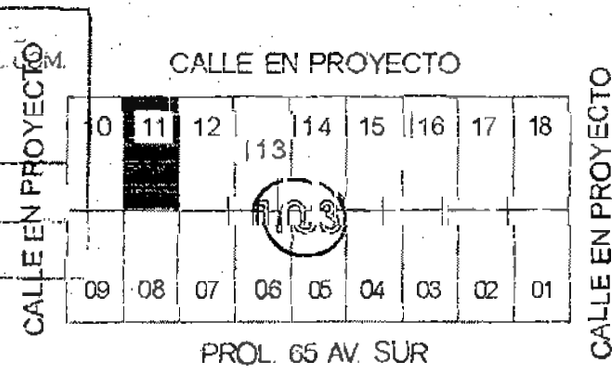

EL CONTENIDO DE ESTE DOCUMENTO REGISTRADO HOY A LAS 14:12 HORAS, BAJO EL NUMERO 171 COMO PARTIDA ____ A FOJAS 605a 606 DEL TOMO CCCVIII, DEL REGISTRO PUBLICO DE LA PROPIEDAD Y DEL COMERCIO DE LA CIUDAD DE Chetumal QUINTANA ROO, A 15 DE Octubre DE 1998 Sección I.

Dirección del Registro Público de la Propiedad y del Comercio
Poder Ejecutivo
Estado de Q. Roo.

DIRECTOR DEL REGISTRO PUBLICO DE LA PROPIEDAD Y DEL COMERCIO

CERTIFICADO DE PROPIEDAD

QUE EL INSTITUTO DE VIVIENDA DE QUINTANA ROO, A TRAVES DEL C. ING. MARIO ERNESTO VILLANUEVA MADRID Y C. LIC. VICTOR MANUEL VIVAS GONZALEZ, EN SUS CARACTERES DE PRESIDENTE Y CONSEJERO VOCAL MUNICIPAL DEL CONSEJO DIRECTIVO DEL INVIQROO Y EN USO DE LAS FACULTADES QUE LES CONFIERE LOS ARTICULOS SEPTIMO Y 13 FRACCION V DE LA LEY DE CREACION DEL PROPIO INSTITUTO, HAN TENIDO A BIEN EXPEDIR EN FAVOR DE:

SOCORRO NIDELVIA TRINCHAN MENDOZA

RESPECTO A UNA SUPERFICIE DE TERRENO DE 220.00 METROS CUADRADOS, MARCADO COMO LOTE 11, MANZANA 103 DE LA RESERVA TERRITORIAL DEL INVIQROO

UBICADA EN LA CIUDAD DE COZUMEL MUNICIPIO DE COZUMEL QUINTANA ROO, CON LAS SIGUIENTES MEDIDAS Y COLINDANCIAS:

AL NORTE: 22.00 MTS. CON LOTE 12
AL SUR : 22.00 MTS. CON LOTE 10
AL ESTE : 10.00 MTS. CON LOTE 08
AL OESTE: 10.00 MTS. CON CALLE

CALLE CATASTRAL: 4012210311

EL PRESENTE CERTIFICADO DE PROPIEDAD, SE EXTIENDE DE CONFORMIDAD A LAS NORMAS ESTABLECIDAS EN EL CODIGO CIVIL VIGENTE Y LA LEY DEL INSTITUTO DE VIVIENDA, AMBAS DEL ESTADO DE QUINTANA ROO Y EN BASE AL EXPEDIENTE RELATIVO AL CONTRATO CELEBRADO EL DIA 30 DE JULIO DE 1991 4 DE OCTUBRE DE 1994 POR EL CUAL EL INVIQROO VENDIO EL LOTE DE TERRENO A SOCORRO NIDELVIA TRINCHAN MENDOZA CON EL FIN DE PROCURAR Y CONSOLIDAR EL PATRIMONIO INMOBILIARIO DE LA FAMILIA QUINTANARROENSE.

DADO EN LA CIUDAD DE CHETUMAL MUNICIPIO DE OTHON P. BLANCO ESTADO DE QUINTANA ROO, A LOS OCHO DIAS DEL MES DE JUNIO DE MIL NOVECIENTOS NOVENTA Y OCHO

PRESIDENTE DEL CONSEJO

ING. MARIO VILLANUEVA MADRID

CONSEJERO MUNICIPAL

LIC. VICTOR MANUEL VIVAS GONZALEZ

ESTADOS UNIDOS MEXICANOS

Despacho ... Ciudad Che... Quintana Roo, Méx.

No. DE FOLIO 2203

PARA LOS EFECTOS LEGALES QUE PROCEDAN, EL INVIQROO MANIFIESTA:

1.-QUE LA FRACCION DE TERRENO OBJETO DE ESTE CERTIFICADO DE PROPIEDAD, SE ENCUENTRA DENTRO DE UNA SUPERFICIE MAYOR DE SU PATRIMONIO, TAL Y COMO CONSTA, POR LA EXHIBICION DE LA ESCRITURA PUBLICA NUMERO 2255 DE FECHA 10 DE SEPTIEMBRE DE 1986 MISMA QUE SE HAYA INSCRITA EN EL REGISTRO PUBLICO DE LA PROPIEDAD Y DEL COMERCIO DE LA CIUDAD DE CHETUMAL, QUINTANA ROO, EL DIA 25 DE AGOSTO DE 1987, BAJO EL NUMERO 45 A FOJAS 170 A 173 DEL TOMO I SECCION QUINTA.

2.- QUE LA SUBDIVISION DE LA SUPERFICIE MAYOR ENUNCIADA EN LA DECLARACION QUE ANTECEDE, QUEDO INSCRITA A FOJAS 17 A 36 DEL TOMO CCLXXIX SECCION PRIMERA DEL REGISTRO PUBLICO DE LA PROPIEDAD Y DEL COMERCIO DE LA CIUDAD DE CHETUMAL QUINTANA ROO Y DE LA QUE RESULTA EL LOTE DE TERRENO QUE SE DESINCORPORA DE SU PATRIMONIO.

3.- QUE SE CONVINO COMO PRECIO DE LA OPERACION CITADA EN EL CONTRATO DE COMPRAVENTA CON RESERVA DE DOMINIO Y CONVENIO MODIFICATORIO LA CANTIDAD DE $ 3,425.4

CANTIDAD QUE EL INVIQROO HA RECIBIDO EN BUENAS MONEDAS DE CURSO LEGAL. Traspasado Virtualmente 17/11/04

CROQUIS DE LOCALIZACION

REG. PUBLICO DEL COM.
TRASPASO
NÚM. FOLIO
FECHA
CHETUMAL, Q. ROO

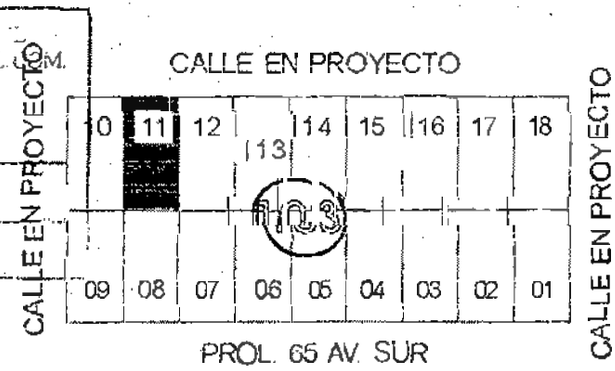

EL CONTENIDO DE ESTE DOCUMENTO REGISTRADO HOY A LAS 14:12 HORAS, BAJO EL NUMERO 171 COMO PARTIDA ____ A FOJAS 605a 606 DEL TOMO CCCVIII, DEL REGISTRO PUBLICO DE LA PROPIEDAD Y DEL COMERCIO DE LA CIUDAD DE Chetumal QUINTANA ROO, A 15 DE Octubre DE 1998 Sección I.

Dirección del Registro Público de la Propiedad y del Comercio
Poder Ejecutivo
Estado de Q. Roo.

DIRECTOR DEL REGISTRO PUBLICO DE LA PROPIEDAD Y DEL COMERCIO